LINTAS

(Layanan Inventaris & Tata Aset Sistem)

Mengubah Data Aset Menjadi Informasi Spasial Dinamis

Aplikasi Tata Kelola Infrastruktur Transportasi Berbasis Geographic Information System (GIS) untuk Dinas Perhubungan Daerah

Smart Governance | Smart Infrastructure | Data-Driven Decision Making

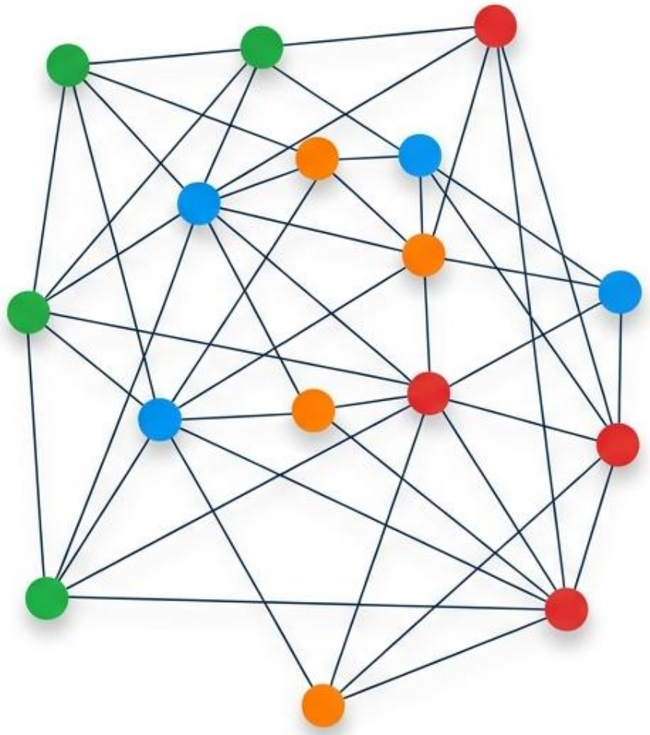

Transformasi Tata Kelola: Manual vs Digital

Aspek	Sistem Lama (Manual)	LINTAS (Digital)
Penyimpanan Data	Dokumen fisik terfragmentasi	Database relasional terpusat
Aksesibilitas	Lambat (pencarian fisik)	Akses instan & real-time via web
Visualisasi	Terbatas pada tabel teks	Peta interaktif geografis (GIS)
Keamanan	Risiko data hilang/terselip tinggi	Backup otomatis & kontrol akses
Analisis	Bergantung survei manual berulang	Monitoring status presisi

LINTAS: Adalah aplikasi Tata Kelola Infrastruktur Transportasi Berbasis Geographic Information System (GIS) untuk Dinas Perhubungan Daerah

LINTAS (Layanan Inventaris & Tata Aset Sistem) mendigitalisasi seluruh data aset ke dalam peta interaktif untuk pengawasan akurat dan manajemen laporan transparan.

Dashboard Monitoring Utama

Fungsi dashboard:
Pusat kendali sistem yang menyajikan visualisasi distribusi aset secara makro di seluruh wilayah Kabupaten/Kota.

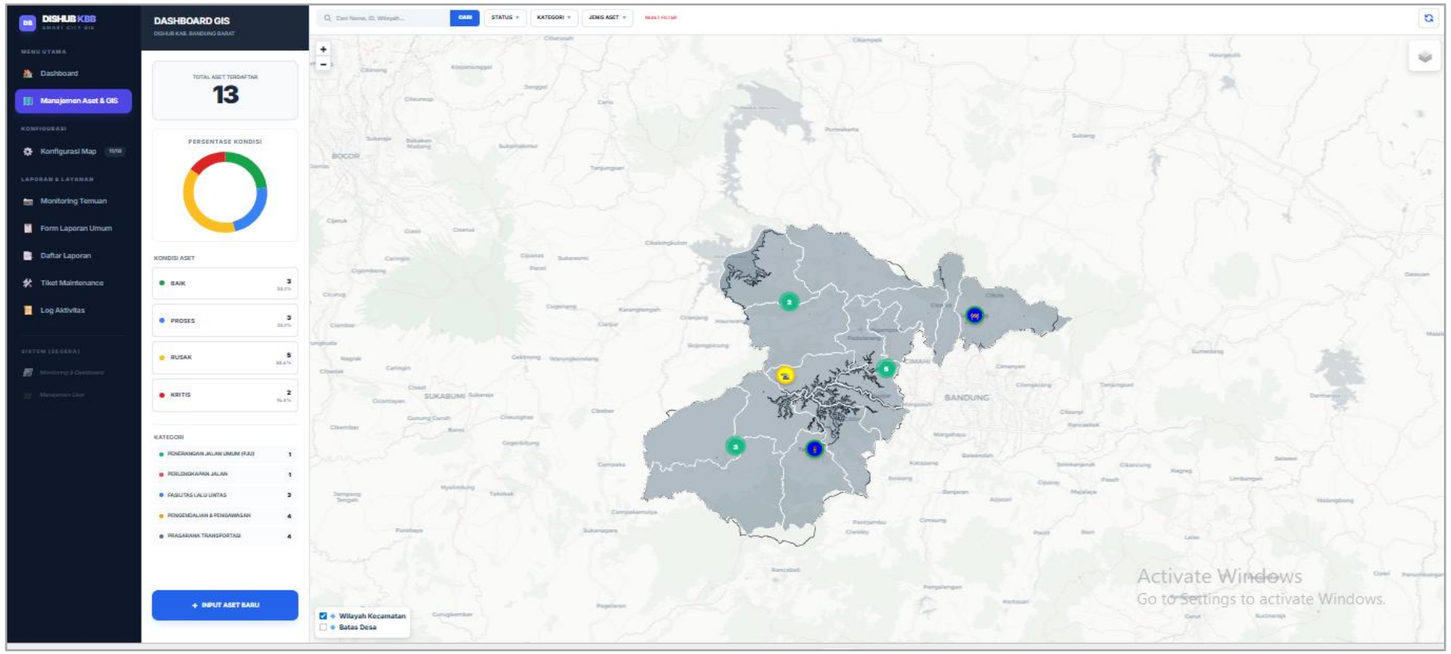

Informasi yang tersedia di dashboard:

- Jumlah total aset per kategori
- Sebaran geografis (titik-titik marker di peta)
- Status kondisi aset (terintegrasi dengan warna marker)

Fitur utama dashboard:

- Menampilkan sebaran seluruh prasarana (PJU, CCTV, rambu, halte, dll.)
- Visualisasi dalam satu tampilan peta terpadu
- Responsif terhadap berbagai perangkat
- **Real-time monitoring** dari seluruh aset

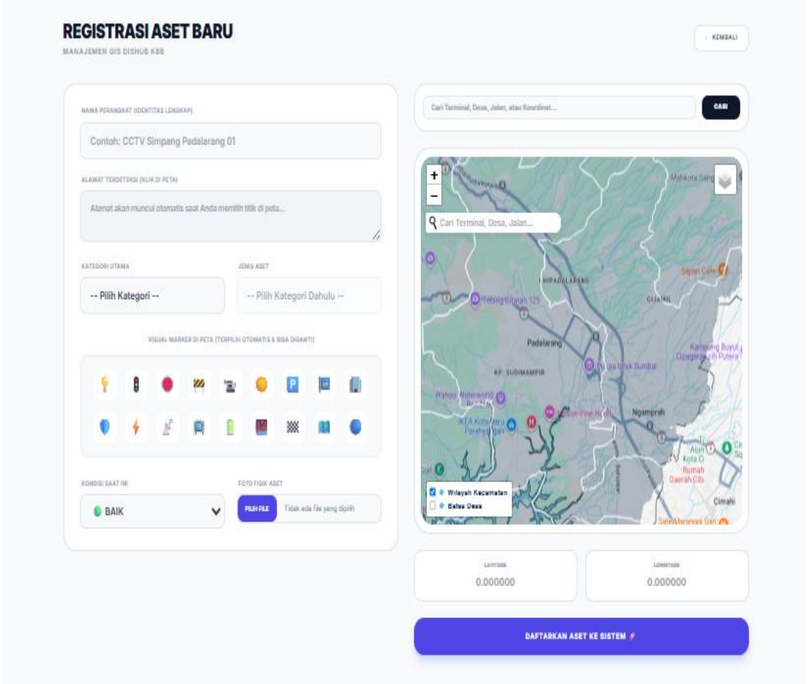

Inventarisasi Lengkap Prasarana dan Perlengkapan Jalan

- **Penerangan Jalan Umum (PJU):** Pemetaan titik lampu jalan di seluruh ruas wilayah.
- **CCTV Monitoring:** Titik koordinat kamera pengawas lalu lintas.
- **Rambu & Marka Jalan:** Inventarisasi rambu petunjuk dan larangan.
- **Fasilitas Lalu Lintas:** Lampu peringatan (Warning Light) dan APILL.
- **Prasarana Transportasi:** Halte, terminal, dan sarana pendukung lainnya.

Sistem menggunakan Custom Marker dinamis untuk memudahkan identifikasi visual pada peta.

Sistem Filter Kondisi: Prioritas Penanganan 4-Tier

BAIK

Aset berfungsi optimal tanpa kendala.

RUSAK

Gangguan fungsi, namun belum masuk tahap darurat.

PROSES

Aset sedang dalam penanganan tim teknis di lapangan.

KRITIS

Rusak berat. High priority. Membutuhkan alokasi anggaran dan penanganan segera.

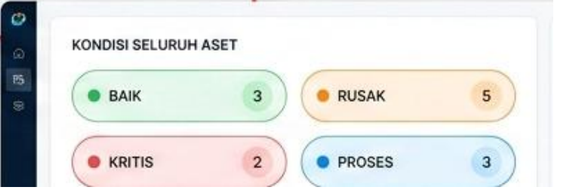

Detail Aset Presisi dalam Satu Klik

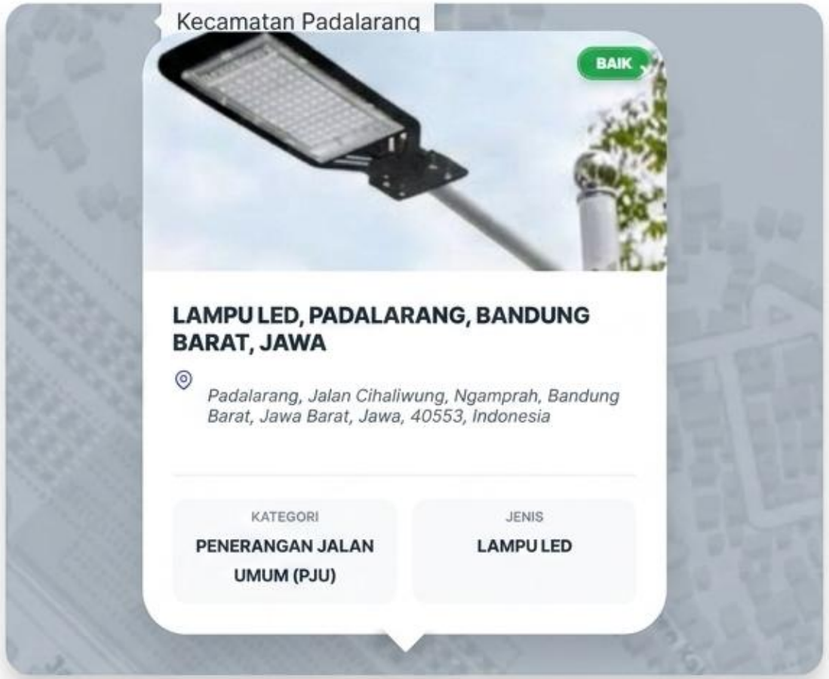

- **Identitas Aset:** Nama, QR Code unik, dan kategori.
- **Lokasi Spasial:** Alamat lengkap dan koordinat geografis presisi.
- **Status Fisik:** Kondisi terkini dengan label warna terintegrasi.
- **Metadata Riwayat:** Tanggal update terakhir dan nama petugas pembaru data.

Single Page Experience – Pemeriksaan mendalam tanpa berpindah halaman.

Portal Pelaporan Inklusif untuk Masyarakat dan Petugas

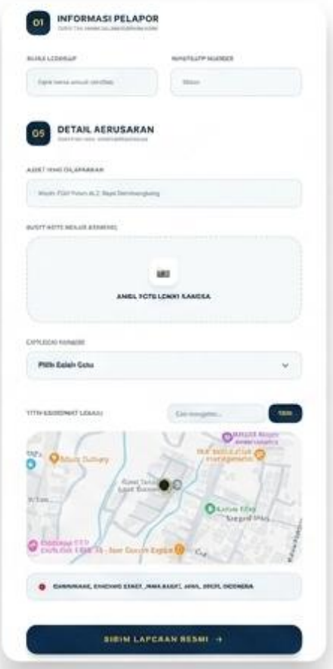

Antarmuka Publik. Warga melapor dengan identitas, lokasi otomatis, dan bukti foto. Cepat dan mudah.

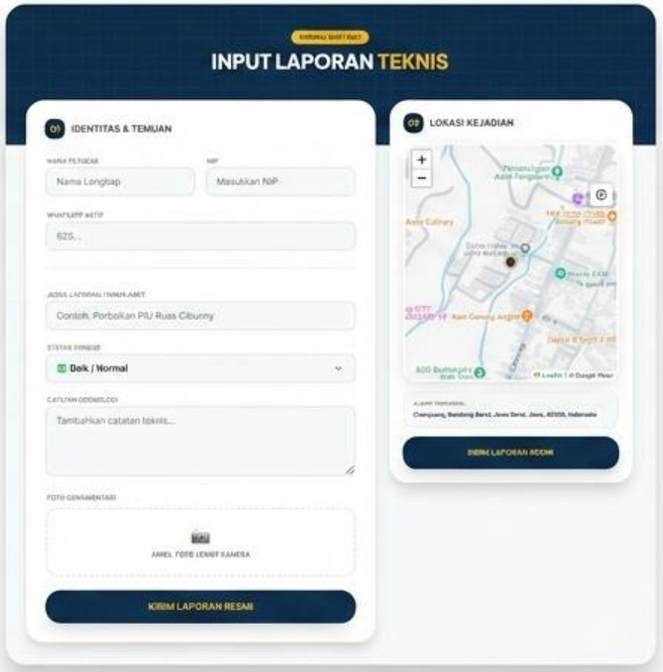

Portal Survei Teknis. Formulir mendalam bagi petugas untuk inspeksi rutin lapangan, mendukung analisis jangka panjang.

Alur Kerja Terintegrasi: Estafet Digital Tanpa Login

Masyarakat melapor via portal web.

→

Laporan masuk sistem + Notifikasi otomatis ke WhatsApp Admin Dishub (via Bot).

→

Admin memvalidasi dan membuat tiket kerja digital di dashboard.

→

Kepala Seksi menerima link tiket di WA.

→

Instruksi & koordinat diteruskan ke WhatsApp Petugas Lapangan untuk eksekusi.

Validasi dan Disposisi Tiket Kerja

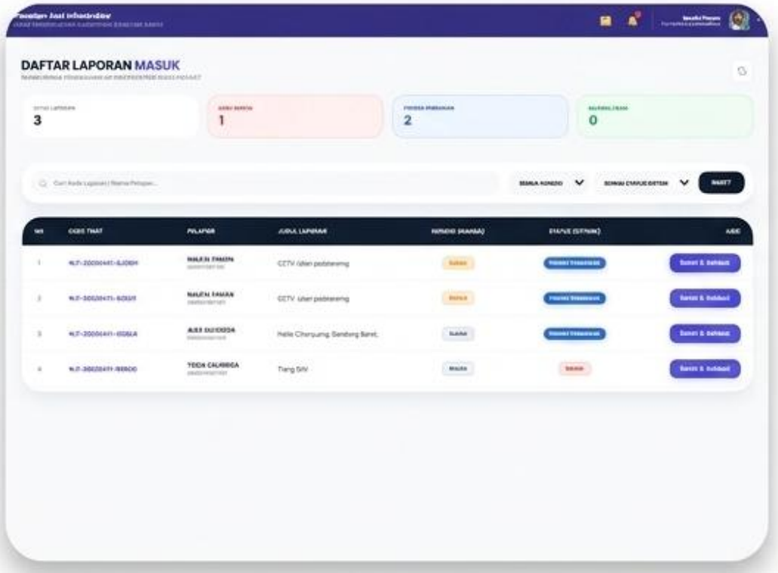

Laporan Masuk

Tiket Kerja Aktif

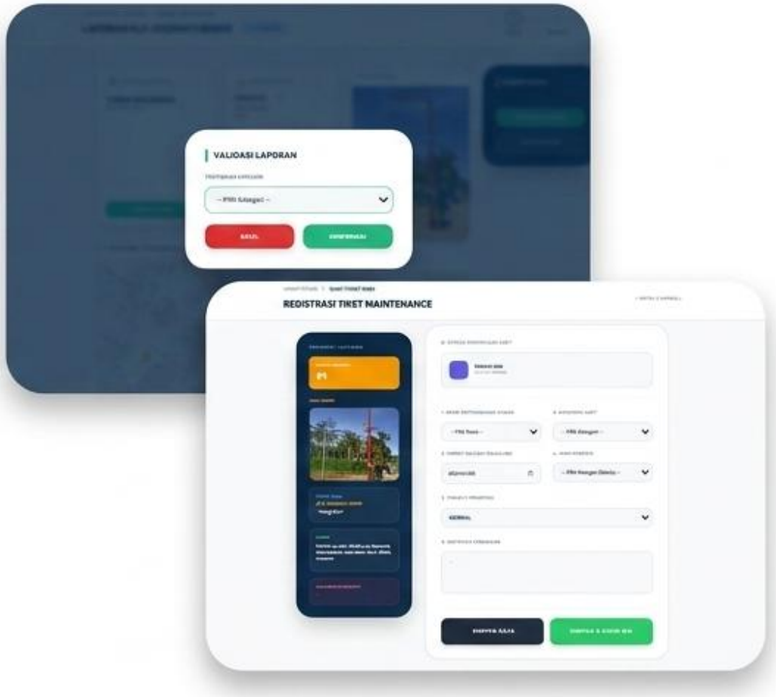

Menampung database laporan masuk masyarakat & temuan petugas.

Protokol validasi ketat. Administrator menentukan tingkat prioritas dan mengalokasikan tugas langsung ke Seksi terkait (misal: Seksi PJU).

Akuntabilitas Terukur: Pelacakan Tiket dan Jejak Digital

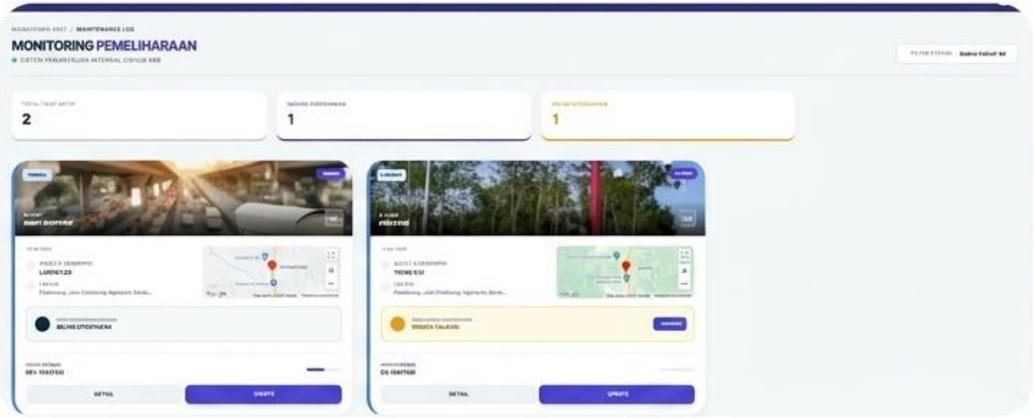

Pemantauan siklus hidup tugas secara real-time (Open -> Proses -> Selesai) untuk menjamin penyelesaian.

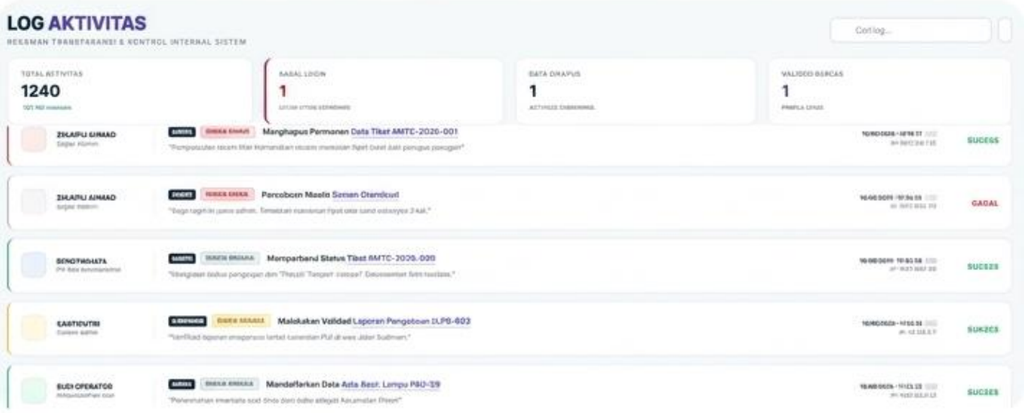

Keamanan transparan. Mencatat seluruh riwayat aktivitas pengguna (**Siapa, Kapan, Apa** yang dilakukan) untuk mencegah manipulasi data.

Dampak Strategis bagi Pemerintah Daerah

Efisiensi Anggaran

Mencegah pemborosan. Skala prioritas perbaikan infrastruktur ditetapkan akurat berdasarkan data tingkat kerusakan ('Kritis'/'Rusak').

Sentralisasi Data

Menghilangkan ego sektoral. Meminimalisir duplikasi pendataan dan mencegah kehilangan aset daerah.

Speed of Response

Memangkas birokrasi. WhatsApp Dispatching memungkinkan penanganan laporan masyarakat dalam hitungan jam.

Data-Driven Decision

Lokasi pemasangan PJU/CCTV baru didasarkan pada visualisasi titik buta pemetaan aktual, bukan perkiraan.

LINTAS

Langkah Awal Mewujudkan Infrastruktur Cerdas

LINTAS membuktikan bahwa transformasi dari pendataan manual ke Sistem Informasi Geografis (GIS) menghasilkan tata kelola yang terukur, respon yang lebih cepat, dan transparansi mutlak. Rekapitulasi data kinerja kini dapat diekspor instan untuk keperluan arsip dan analisis lanjutan.

Geocitra

www.geocitra.com

Kontak:

Taru J. Wisnu (0815 84028188)